令和　４年（ケ）第　　２０号

期　間　入　札　の　公　告

令和　４年　７月１３日
千葉地方裁判所民事第４部
裁判所書記官　根　本　由美子

別紙物件目録記載の不動産を下記のとおり期間入札に付します。

記

入札期間	令和　４年　８月　３日　午前　９時００分から 令和　４年　８月１０日　午後　５時００分まで	
開札期日	日　時 場　所	令和　４年　８月１７日　午前　９時３０分 千葉地方裁判所売却場
売却決定期日	日　時 場　所	令和　４年　８月３１日　午前１０時００分 千葉地方裁判所民事第４部
特別売却実施期間	令和　４年　８月１８日　午前　９時００分から 令和　４年　８月２２日　午後　４時３０分まで	
買受申出の保証の提供方法	下記のいずれかによる。 （１）当裁判所の預金口座に金銭を振り込んだ旨の金融機関の証明書。 （２）銀行，損害保険会社，農林中央金庫，商工組合中央金庫，全国を地区とする信用金庫連合会，信用金庫又は労働金庫の支払保証委託契約締結証明書。	
買受申出の資格の制限（民事執行規則３３条）	☆印を付した物件は農地であるので，権限を有する行政庁の交付した買受適格証明書を有する者及び買受けについて農地法上の許可又は届出を必要としない者に限り，買受申出をすることができます。	
一般の閲覧に供するため，物件明細書・現況調査報告書・評価書の各写しを令和　４年　７月１３日から当庁物件明細書等閲覧室に備え置きます。		

物件番号	売却基準価額（円） 買受可能価額（円）	一括 売却	買受申出保証額（円）	令和３年度	
				固定資産税（円）	都市計画税（円）
2, 3	5, 280, 000 4, 224, 000	一括	1, 056, 000	1, 894	0
2	4, 730, 000				
3	550, 000				
備考					

令和　４年（ケ）第　　２０号

物　件　目　録

２　所　　在　　長生郡長生村一松字砂畑十二

　　地　　番　　戊３４５１番３５

　　地　　目　　雑種地

　　地　　積　　４６３１平方メートル

３　所　　在　　長生郡長生村一松字砂畑十二

　　地　　番　　戊３４５１番３６

　　地　　目　　雑種地

　　地　　積　　５３７平方メートル

令和　4年（ケ）第　　20号

物　件　明　細　書

令和　4年　5月23日
千葉地方裁判所民事第4部
裁判所書記官　中　嶋　路　彦

1　不動産の表示
【物件番号2，3】
別紙物件目録記載のとおり

2　売却により成立する法定地上権の概要
なし

3　買受人が負担することとなる他人の権利
【物件番号2，3】
なし

4　物件の占有状況等に関する特記事項
なし

5　その他買受けの参考となる事項
なし

《注　　意　　書》

1　本書面は，現況調査報告書，評価書等記録上表れている事実等を記載したものであり，関係者の間の権利関係を最終的に決める効力はありません（訴訟等により異なる判断がなされる可能性もあります）。

2　記録上表れた事実等がすべて本書面に記載されているわけではありませんし，記載されている事実や判断も要点のみを簡潔に記載されていますので，必ず，現況調査報告書及び評価書並びに「物件明細書の詳細説明」も御覧ください。

3　買受人が，占有者から不動産の引渡しを受ける方法として，引渡命令の制度があります。引渡命令に関する詳細は，「引渡命令の詳細説明」を御覧ください。

4　対象不動産に対する公法上の規制については評価書に記載されています。その意味内容は「公法上の規制の詳細説明」を御覧ください。

5　各種「詳細説明」は，閲覧室等に，別ファイルとして備え付けられています。

令和　４年（ケ）第　　２０号

物　件　目　録

２　所　　在　　長生郡長生村一松字砂畑十二

　　地　　番　　戊３４５１番３５

　　地　　目　　雑種地

　　地　　積　　４６３１平方メートル

３　所　　在　　長生郡長生村一松字砂畑十二

　　地　　番　　戊３４５１番３６

　　地　　目　　雑種地

　　地　　積　　５３７平方メートル

令和４年(ケ)第２０号
令和４年３月８日受理
令和４年４月１９日提出

現況調査報告書

２分冊のうち２（物件２、３）

千葉地方裁判所
執行官　中　　村　　貢

（注）チェック項目中の調査結果は，「■」の箇所の記載のとおり

令和　４年（ケ）第　　２０号

物　件　目　録

1　所　　在　　長生郡長生村一松字砂畑十二

地　　番　　戊３４５１番２７

地　　目　　田

地　　積　　１３７６平方メートル

所有者　Ａ

2　所　　在　　長生郡長生村一松字砂畑十二

地　　番　　戊３４５１番３５

地　　目　　雑種地

地　　積　　４６３１平方メートル

所有者　東葉興業株式会社

3　所　　在　　長生郡長生村一松字砂畑十二

地　　番　　戊３４５１番３６

地　　目　　雑種地

地　　積　　５３７平方メートル

所有者　東葉興業株式会社

4　所　　在　　長生郡長生村一松字砂畑十二

地　　番　　戊３４５１番１１７

地　　目　　田

地　　積　　３０２２平方メートル

所有者　Ａ

（土地用）

不動産の表示	「物件目録」のとおり
住居表示	未実施
土地	物件２、３
現況地目	□宅地（物件　　）　□公衆用道路（物件　　）　□農地（物件　　） ■雑種地（物件２、３）　□山林　　（物件　　）　□ □
形状	■公図のとおり　□地積測量図のとおり □建物図面（各階平面図）のとおり　□土地建物位置関係図のとおり □
占有者及び占有状況	■土地所有者　□その他の者 □上記の者が本土地上に、下記目的外建物を所有し、占有している □上記の者が駐車場として使用し、占有している ■上記の者が雑草を繁茂させた更地の状態で占有している。 □ □「占有者及び占有権原」のとおり □
その他の事項	
執行官保管の仮処分	■ない □ある　[　　地方裁判所　　支部　平成　　年（　）第　　号 保管開始日　平成　　年　　月　　日
建物（目的外建物）	■ない □ある（詳細は「目的外建物の概況」のとおり）
土地建物の位置関係	□建物図面（各階平面図）のとおり　□土地建物位置関係図のとおり

（注）チェック項目中の調査結果は，「■」の箇所の記載のとおり

関係人の陳述等

陳述者 （当事者等との関係）	陳述内容等
■所有者会社元従業員	本土地は何も使ってません。境界紛争はありません。前は何に使われていたのかはわかりません。

（注）チェック項目中の調査結果は，「■」の箇所の記載のとおり

執 行 官 の 意 見

第１　本物件の状況は別紙公図、一筆図形（地籍調査成果図、長生村役場提出）及び別添写真のとおりである。

第２　物件２、３について

１　物件２、３は一体の土地となっており、西側が水路を介して未舗装の公衆用道路及び北側が水路敷きに面する長方形の概ね平坦な土地となっている。水路に面する西側及び北側については本土地の範囲を確認することは可能である。東側には一部コンクリートの縁石が設置されている。同縁石部分を除き南側及び東側は隣地と一体となり、ブロック等の設置物も存在しないことから、同部分における範囲を目視により確認することはやや困難であるものの、別紙一筆図形（地籍調査成果図、長生村役場提出）と対比することにより同部分におけるおおよその範囲を確認することは可能である。

２　本土地はやや盛土の状態となっている。盛土の内容物は不明である。

３　本土地の南西側角の水路敷きに本土地と西側公衆用道路を渡す路橋が存在する。

４　本土地は雑草が繁茂、密生した状態であったこと、第３者の占有を示す徴表は窺えなかったこと及び「関係人の陳述等」記載の関係人の陳述から本土地は所有者会社が更地の状態で占有するものと認められる。なお、千葉地方法務局茂原支局から本土地上の建物登記は存在しない旨回答を受けた。

（注）チェック項目中の調査結果は，「■」の箇所の記載のとおり

（調査経過用）

調 査 の 経 過		
調 査 の 日 時	調 査 の 場 所 等	調 査 の 方 法 等
4年3月9日（水）	執行官室	長生村役場に対し、地番図、一筆図形（地籍調査成果図）送付嘱託
4年3月10日（木） 12：30－12：38	物件所在地	物件確認（以後予定の別件期日のため調査中断）
4年3月17日（木）	執行官室	長生村役場から一筆図形（地籍調査成果図）到着
4年3月18日（金）	執行官室	長生村役場から地番図到着
4年3月22日（火）	執行官室	千葉地方法務局茂原支局に対し、隣地の不動産登記記録全部事項証明書、本土地上の建物の不動産登記記録全部事項証明書各送付嘱託
4年3月24日（木）	執行官室	千葉地方法務局茂原支局から隣地の不動産登記記録全部事項証明書到着、本土地上の建物登記なしの回答受送付
4年3月25日（金） 16：50－17：18	物件所在地	物件調査、写真撮影
4年4月1日（金） 13：41－13：50	当職携帯電話	所有者会社元従業員に架電、占有関係聴取

（注）チェック項目中の調査結果は，「■」の箇所の記載のとおり

公　図　写

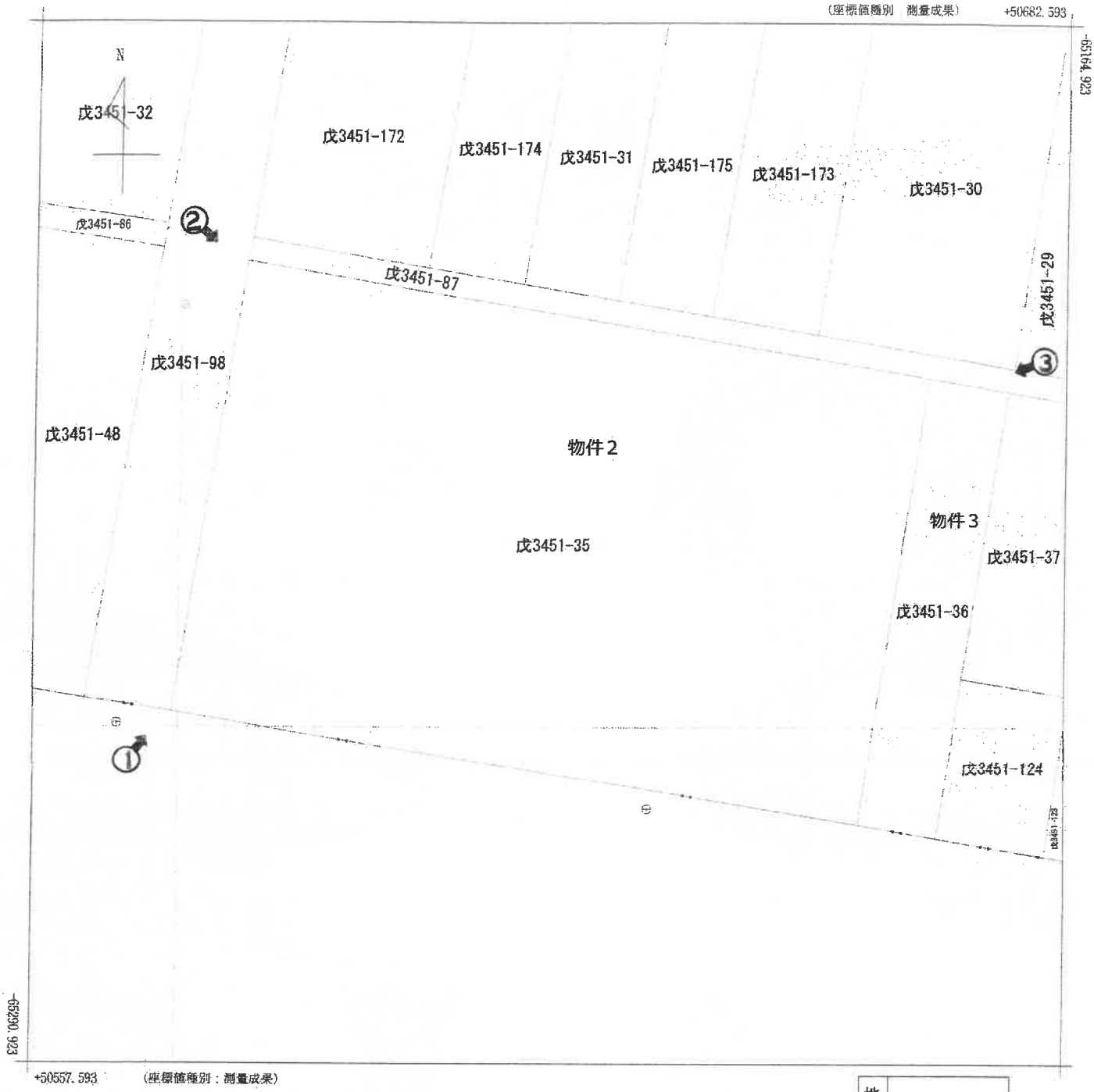

地番区域見出	一松

(注) ○→は写真撮影位置，方向及び写真番号を示す

請求部分	所在	長生郡長生村一松字砂畑十二				地番	戊3451番35		
出力縮尺	1/500	精度区分	甲三	座標系番号又は記号	Ⅸ	分類	地図(法第１４条第１項)	種類	地籍図
作成年月日				備付年月日(原図)		補記事項			

これは地図に記録されている内容を証明した書面である。

(Ａ３判をＡ４判に縮小した)

令和3年12月6日
千葉地方法務局茂原支局
登記官

請求番号：12-4

(1/1)

(　6　枚目)

[redacted]

S=1：500　　一　筆　図　形　　令和4年3月14日　　ページ1

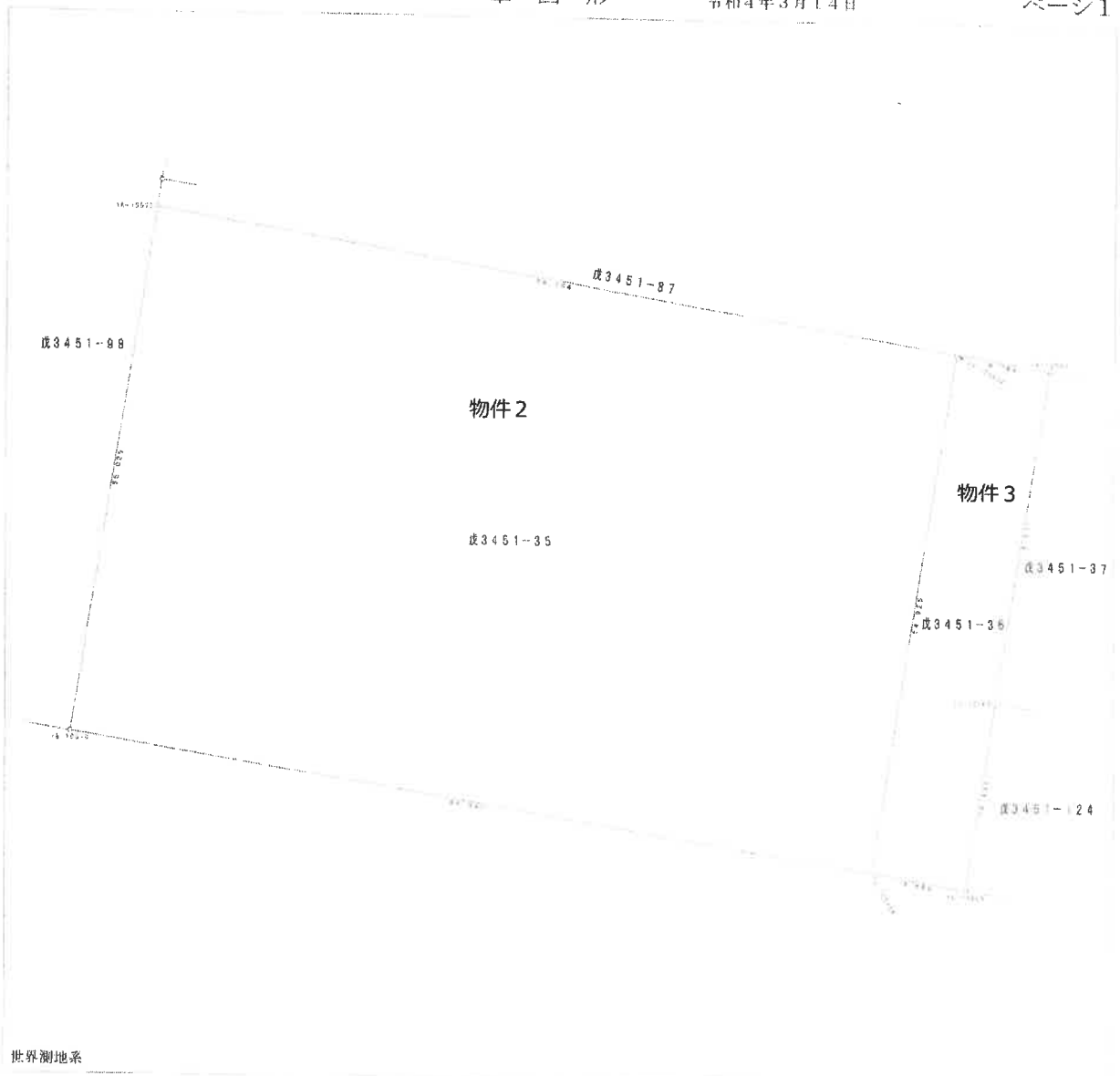

世界測地系

地番一覧表

所在	一松字砂畑十二
地番	戊3451-35
登記地目	雑種地
登記面積	4691㎡

所在　一松字砂畑十二　地番　戊3451-35

点番	X座標値	Y座標値
16-10563K	-65207.789	50665.998
16-10569K	-65262.033	50657.373
16-10570	-65248.128	50574.187
16-10573	-65193.814	50583.002

地番一覧表

所在	一松字砂畑十二
地番	戊3451-36
登記地目	雑種地
登記面積	537㎡

所在　一松字砂畑十二　地番　戊3451-36

点番	X座標値	Y座標値
16-10563	-65209.410	50675.627
16-10564	-65244.045	50670.120
16-10569	-65263.657	50667.086
16-10569K	-65262.033	50657.373
16-10563K	-65207.789	50665.998

基準点番号	X座標値	Y座標値
P06P004107-1	-65190.083	50575.275
P06P004110-1	-65260.057	50631.697
P06Z414	-65249.554	50567.635

（７枚目）

（Ａ３判をＡ４判に縮小した）

※この図面は地籍調査完了時点です

長生村長 [redacted]

1

2

3

令和 4年 (ケ) 第 20 号
令和 4年 3月15日 現地調査
令和 4年 4月 8日 評 価
第 1351 号 −2 発行番号
令和 4年 4月13日 提 出 日

千葉地方裁判所
民事第4部 御中

評 価 書

2分冊の2
(物件2・3)

評価人 不動産鑑定士

富 井 康 司 印

第１　評価額

一　括　価　格	
金５，２８０，０００円	
内　訳　価　格	
物件２（土地）	金４，７３０，０００円
物件３（土地）	金５５０，０００円

①　一括価格は，物件２・３の各不動産について，一括売却（民事執行法６１条本文）を行うことを前提とした場合の価格である。
②　内訳価格は，配当等の判断のために一括価格の内訳として算出した価格である。

第２　評価の条件

１．本件価格は，民事執行法により売却に付されることを前提とした適正価格を求めるものである。
　したがって，求めるべき評価額は，一般の取引市場において形成される価格ではなく，一般の不動産取引と比較しての競売不動産特有の各種の制約（売主の協力が得られないことが常態であること，買受希望者は内覧制度によるほかは物件内部の確認が直接できないこと，引渡しを受けるために法定の手続をとらなければならない場合があること，目的物の種類又は品質に関する不適合には担保責任がないこと等）等の特殊性を反映させた価格とする。

２．評価は，目的物件の調査時点における現状に基づいて行うものであり，調査日以降発生した物件の現状変更については原則として考慮していない。

３．現地での物件調査は，原則として目視可能な部分に限定される。

４．物件に関する情報提供の内容は，民事執行法５８条４項に定める場合を除いて，原則として公共機関で公開された資料に基づくものである。

第３　目的物件

<table>
<tr><td>番　号</td><td>所在等</td><td colspan="2">登　　記</td><td>現　　況</td></tr>
<tr><td>2</td><td colspan="3" rowspan="2">物件目録記載のとおり。</td><td>（住居表示未実施区域）
同　　左</td></tr>
<tr><td>3</td><td>同　　左</td></tr>
<tr><td>番　号</td><td colspan="4">特　　記　　事　　項</td></tr>
<tr><td></td><td colspan="4">な い。</td></tr>
</table>

現況欄に記載のない事項については，ほぼ登記と同じ。

令和　４年（ケ）第　　２０号

物　件　目　録

1　所　　在　　長生郡長生村一松字砂畑十二

地　　番　　戊３４５１番２７

地　　目　　田

地　　積　　１３７６平方メートル

所有者　Ａ

2　所　　在　　長生郡長生村一松字砂畑十二

地　　番　　戊３４５１番３５

地　　目　　雑種地

地　　積　　４６３１平方メートル

所有者　東葉興業株式会社

3　所　　在　　長生郡長生村一松字砂畑十二

地　　番　　戊３４５１番３６

地　　目　　雑種地

地　　積　　５３７平方メートル

所有者　東葉興業株式会社

4　所　　在　　長生郡長生村一松字砂畑十二

地　　番　　戊３４５１番１１７

地　　目　　田

地　　積　　３０２２平方メートル

所有者　Ａ

第４　目的物件の位置・環境等

土地の概況及び利用状況等(物件２・３の一体地)

<table>
<tr><td>位置・交通</td><td colspan="2">ＪＲ外房線「八積」駅から東方へ道路距離で約5.2km。路線バス「一ツ松海岸」停からは南東方へ同約830m。
(別添「所在位置略図」参照)</td></tr>
<tr><td>付近の状況</td><td colspan="2">主要地方道飯岡一宮線と九十九里道路に挟まれた雑種地や山林が広がる中，別荘が介在するリゾート地域。</td></tr>
<tr><td>主な公法上の規制等
(道路の幅員等の個別的な規制を考慮しない一般的な規制)</td><td>都市計画区分
用途地域
建蔽率
容積率
防火規制
その他の規制</td><td>非線引き都市計画区域
第２種住居地域
指定６０％
指定２００％
－
日影規制(5-3h)，県立九十九里自然公園普通地域。</td></tr>
<tr><td>画地条件</td><td colspan="2">形状(長方形)　地勢(若干の起伏があるが概ね平坦)
接道方位(西側で小水路を介する)　間口(約55m)
奥行(約94m)　地積(5,168㎡(登記とほぼ同じ))</td></tr>
<tr><td rowspan="4">接面道路の状況</td><td colspan="2">村道(1057号)，幅員(約4m以上。特記事項参照)，連続性(劣)，舗装(無)，歩道(無)，側溝(小水路有)，高低差(2m前後高い)</td></tr>
<tr><td>建築基準法上の種類</td><td>第42条1項1号</td></tr>
<tr><td>セットバック</td><td>－</td></tr>
<tr><td>建物建築の可否</td><td>可（但し，特記事項参照）</td></tr>
<tr><td>土地の利用状況等</td><td colspan="2">雑草が繁茂し，僅かに樹木も見られた。田を盛り土した雑種地で利用されていない。
隣接は，北側が小水路を介して太陽光発電所，東・西・南側が小水路を介するなどして雑種地。</td></tr>
<tr><td>供給処理施設
(敷地内までの引き込みを基準に，引き込みが有る</td><td colspan="2">上水道：なし
ガス配管：なし
下水道：なし</td></tr>
</table>

場合を「あり」，無い場合を「なし」とした。）	
土　壌　汚　染　等	・　土壌汚染の可能性（田を盛り土した雑種地で，盛り土内容が不明のため汚染の可能性は不明） ・　埋蔵文化財包蔵地指定（無） ・　外観からは，地下埋設物の存在が推せられるものは見られなかった。
特　記　事　項	・　西側村道は，現在整備工事中で幅員確定未済だが4m以上は確保され，建築基準法第42条1項1号となる予定（村まちづくり課）とのこと。 ・　南側隣接に村道1050号線があるが，道路形態はなく建築基準法外（村まちづくり課，県長生土木事務所建築宅地課とも同回答）。但し，西端部にある小水路に橋が架かっており，本件土地への出入りはこれを利用している。 ・　隣接小水路は，排水路。 ・　千葉県「ちば情報マップ」のハザードマップでは，津波浸水想定区域に入っている。また，本件土地を除く周囲は洪水浸水想定区域にも該当している。 ・　開発に当たっては，その用途等によって接道等の各種要件具備が必要となる場合がある点，留意のこと。

第５　評価額算出の過程

１　基礎となる価格

物件２・３（土地）

目的土地の更地価格を次のとおり求めた。

物件番号	標準画地価格（円／㎡）ア	個別格差イ	地積（㎡）ウ	建付減価補正率エ	更地価格（円）（千円未満四捨五入）ア×イ×ウ×エ＝オ
2	9,060	23%	4,631	―	9,650,000
3	9,060	23%	537	―	1,119,000

ア　標準画地価格（公示価格等からの規準）

・基準地（長生（県）－１）

価　格　　時点修正　標準化補正　地域格差　　標準画地価格

11,400円/㎡ × 99.3／100× 100／100× 100／125 ≒ 9,060円／㎡

◇時点修正：公示価格等の価格時点から評価日までの推定変動率である。

◇標準化補正（相乗）：無

◇地域格差（相乗）：街路，交通接近，環境，行政的条件格差等を考慮した。

標準画地は，近隣地域において，土地の概況（間口，奥行き，規模等）及び利用状況等が標準的な中間画地（宅地）を想定した。

イ　個別格差（相乗）：物件２・３の一体地

接道状況が劣る　-10%

雑種地　　-50%

規模大　　-50%　（90%×50%×50%≒23%）

ウ　地　積：登記簿数量による。

エ　建付減価補正率：－%

２　評価額の判定

前記により求めた価格に競売市場修正等を施して，下記のとおり評価額を求めた。

物件番号	基礎となる価格（円）ア	占有減価修正ウ	市場性修正率エ	競売市場修正率オ	評価額（円）（1万円未満四捨五入）（ア±イ）×ウ ×エ×オ
2	9,650,000	―	70%	70%	4,730,000
3	1,119,000	―	70%	70%	550,000
一括価格（合計）					5,280,000

ウ 占有減価修正：特にない。

エ 市場性修正：雑種地の取引であり，場所的にも市場性が劣ると判断して▲30％の修正を施した。

オ 競売市場修正率：第２評価の条件欄記載の不動産競売市場の特殊性等を考慮した。

第６　参考資料

・基準地(長生(県)－１)

所　　在	長生郡長生村驚字十二号587番2外
価　　格	11,400円／㎡
位　　置	ＪＲ外房線「八積」駅から5.5km。
価格時点	R3.7.1
地　　積	369㎡
供給処理施設	上水・下水
接面街路	東5m村道
用途指定等	非線引き都市計画区域，第２種住居地域(60，200)
地域の概要	中小規模の一般住宅，スパ施設が混在する海岸に近い住宅地域。

第７　附属資料

１　目的物件の所在位置略図

２　公図写

以　　上

所在位置略図

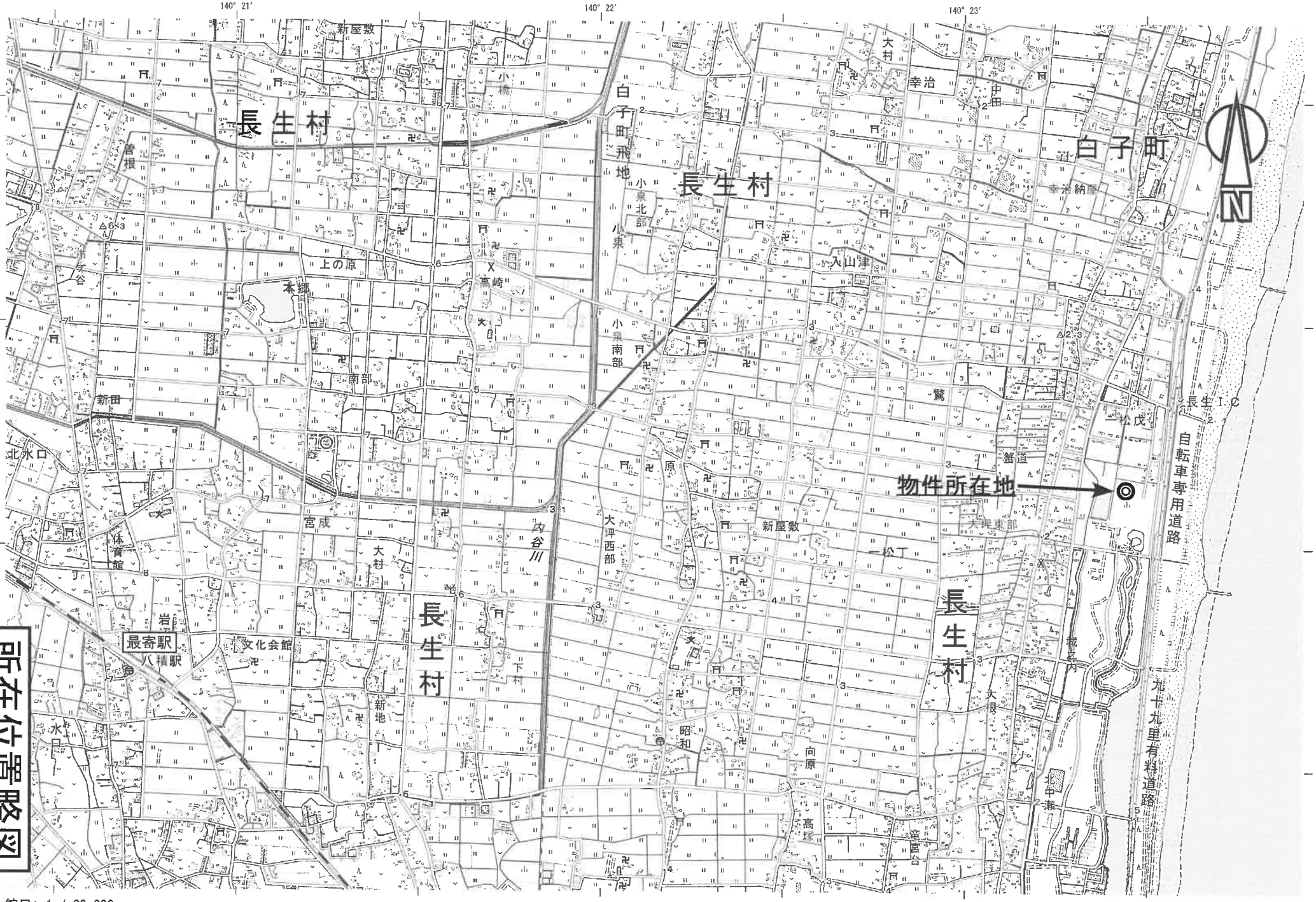

縮尺: 1 / 20,000

国土地理院地形図写(地理院タイルを加工)

戊3451-173
戊3451-30
戊3451-86
戊3451-87
戊3451-29
戊3451-98
戊3451-48
物件(2)
戊3451-35
戊3451-37
物件(3)
戊3451-36
34-83
公図境
丁3684-84
公図写
N
1/500